ME(569.4)נכ
ד/1780

ד/1780

מיכה, צבי ן לבנון, אמנס
דו"ח על אפיונית קיומאטית שנוצע בחצר
קיבוץ רמת.

המכון הגיאופיסי בישראל

א. **מטרת הסקר:**

בהזמנת מר אושפיז מועד קריית-חיים, מפעל המים, בוצעה סדרת מדידות התנגדות חשמלית בקריית-חיים.

מטרת המדידות הגיאוחשמליות היתה באם ניתן יהיה לקבוע בעזרתן את כדאיות העסקה של באר א', השואבת עתה מעומק של 18 מ', על מנת שתשמש כמליפה לבאר כג' החדשה ומשלימה.

למטרות קורלציה בעמו מדידות ליד הבארות כג' וכג'.

ב. **משמעות המדידות הגיאוחשמליות:**

המדידות הגיאוחשמליות נעשות על פני הקרקע, והן קובעות את התנגדות שם-הקרקע לזרם חשמלי.

תוצאות המדידות מצורפות לדו"ח זה בצורת עקומות המראות את השינויים בהתנגדות החשמלית היחסית מפני הקרקע עד לעומק הנמדד. כדי לקבל את ההתנגדות הסגולית של כל שכבה ושכבה מעבדים את העקומות עיבוד מחשבי, והתוצאות רשומות בטולי העקומות בצורת טולמות של ערכי ההתנגדות המחושבת. על יסוד גובה ההתנגדויות המחושבות וסדרן אפשר להסיק מסקנות על הרכב השכבות בתת-הקרקע ועל טיבן ההידרולוגי.

ג. **תוצאות המדידות ובמובי הבארות:**

מר שרתם, מהשרות ההידרולוגי, מסר לנו את הנתונים המצורפים:

1. **מדידת מס' 3-457 קורלטיבית לבאר כג':**

גובה פני הקרקע 6.66+ מ'.

בתאריך 6.2.56 נמדדה נפילה של 11.23 מ' בספיקה של 92 מ^3/ש עם תכולת כלור של 250 מ"ג/ליטר.

תכולת הכלור כיום (אינפורמציה בעל-פה מאת מר אושפיז) היא 340-360 מ"ג/ליטר. בספיקה של 30 מ^3/ש.

המדידה ליד באר זו מסמה כבטיח לקורלציה ומענות יתר הנתונים באזור הנסקר, שכן קיים חתך ליתולוגי מפורט עד לעומק של 81.50 מ'.

3/....

<u>התאור הליתולוגי</u>

15 - 0 מ'	חול ואבן-חול,
22 - 15 מ'	חרסית,
74 - 22 מ'	אבן-חול,
76 - 74 מ'	חרסית,
80 - 76 מ'	אבן-חול,
81.50 - 80 מ'	חרסית.

<u>חתך ההתנגדויות החשמליות:</u>

7 - 0 מ'	50,000	אום/ס"מ, אפייני לחול או אבן-חול,
26 - 7 מ'	ירידה ל- 5,600	אום/ס"מ, אפייני לחרסית חולית או חול חרסיתי,
75 - 26 מ'	עליה ל- 200,000	אום/ס"מ, אבן-חול,
110 - 75 מ'	ירידה ל- 500	אום/ס"מ, חרסית, או קירטון

ההתאמה בין חתך ההתנגדויות החשמליות והחתך הליתולוגי נראית לנו סבוה ביחס, בהתחשב עם העובדה שבמחים שונים נדגמים ע"י קדוח ומדידה גיאופיסית ובהתאם לכך אנו סבירים שיש בידינו לתת חתך גיאולוגי משוער ושמורם למדי במדידות האחרות.

2. <u>מדידה מס' 1-457 שרלמיביה לצפון מ'</u>

גובה פני הקרקע 3.99+ מ'.

עומק נוכחי 18 מ' (העומק בזמן סתרת הבאר היה 26.90 מ'). גובה פני מים סטטיים (לא בזמן שאיבה) בתאריך 19.11.54 היה 2.04+ מ' מעל פני הים. בתאריך 25.4.54 נמדדה נפילה של 4.71 מ' בשאיבה של 75 $מ^3$/לשעה.

<u>חתך ההתנגדויות החשמליות:</u>

15 - 0 מ'	47,000	אום/ס"מ - חול,
25 - 15 מ'		התנגדות נמוכה מאד - בעיקר חרסית,
75 - 25 מ'	עליה ל- 100,000	אום/ס"מ - חול ואבן-חול,
150 - 75 מ'	ירידה ל- 1,000	אום/ס"מ - חרסית, או קירטון

3. <u>מדידה מס' 2-457 שרלמיביה לצפון מ':</u>

(אינפורמציה בעל-פה ע"י מר אושפיז)

עומק הקדוח 74 מ', פני המים 4.36 מ' שלא בזמן השאיבה. נפילה של 8 - 7 מ' בזמן השאיבה.

4/...

טליחות המים היא 220 מ"ג כלור/ליטר ללא שנוי לפי שעה. מדידה זו נעשתה גם היא למטרת השוואה, למרות שאין בידינו אלא נתוני הצנור בקדוח -

אשדוד "12 עד 70 מ'

חרירי "10 עד 74 מ'.

לדבריו של מר שוהם התחך דומה לזה שבאר כג'.

<u>תחך ההתנגדויות התשטילות:</u>

17 - 0 מ'	39000 אום/ס"מ - חול,
23 - 17 מ'	ירידה ל- 1600 אום/ס"מ - בעיקר חרסית,
62 - 23 מ'	עליה ל- 60000 אום/ס"מ - בעיקר חול ואבן-חול (עם שכב חרסית),
92 - 62 מ'	עליה ל- 200000 אום/ס"מ- בעיקר אבן-חול,
150 - 92 מ'	התנגדות נמוכה - חרסית, אל ודאי.

4. <u>מדידה מס' 4 - 457</u> (ליד הכלגיה 100 מ' מערבה מבנין המשרה).

מדידה זו נוצעה למטרת קבלת אינפורמציה מוקדמת לנקודת קדוח אפשרית בעתיד.

<u>תחך ההתנגדויות התשטילות:</u>

9 - 0 מ'	31000 אום/ס"מ - חול,
28 - 9 מ'	ירידה ל- 5500 אום/ס"מ - בעיקר חרסית,
65 - 28 מ'	התנגדות גבוהה מאד - בעיקר חול ואבן-חול,
82 - 65 מ'	33000 אום/ס"מ או פחות - חול חרסיתי , (?)
93 - 82 מ'	גבוה מאד - אבן-חול,
150 - 93 מ'	ירידה ל- 2000 אום/ס"מ - חרסית, אל ודאי.

התחך המסומן של נקודה זו מראה שיש לצפות לשכבות נקבוביות עד לעומק של 65 מ' בערך. בעומק של 82 - 65 מ' קיימת שכבת ביניים העלולה להיות חרסיתית ומפחתית שכבת חולית עד לעומק של 93 מ' בערך.

ד. <u>מ כ ו ם:</u>

1. בהתאם לנתונים שבידנו במדידה מס' 1-457 (קורלטיבית לבאר א') יש להניח שעד עומק של 75 מ' בערך אפשר לצפות למציאות חול ואבן-חול, ובהתאם לכך נראה לנו שיש להבנן קדוח במקום לעומק זה.

2. במדידה מס' 4-457 (ליד הכלגיה) אין להבנן קדוח לעומק רב יותר מאשר 93 מ' בערך, שכן בעומק זה מתחילות שכבות חרסיתיות.

אזור, 15 בדצמבר 1963.

בכבוד רב,

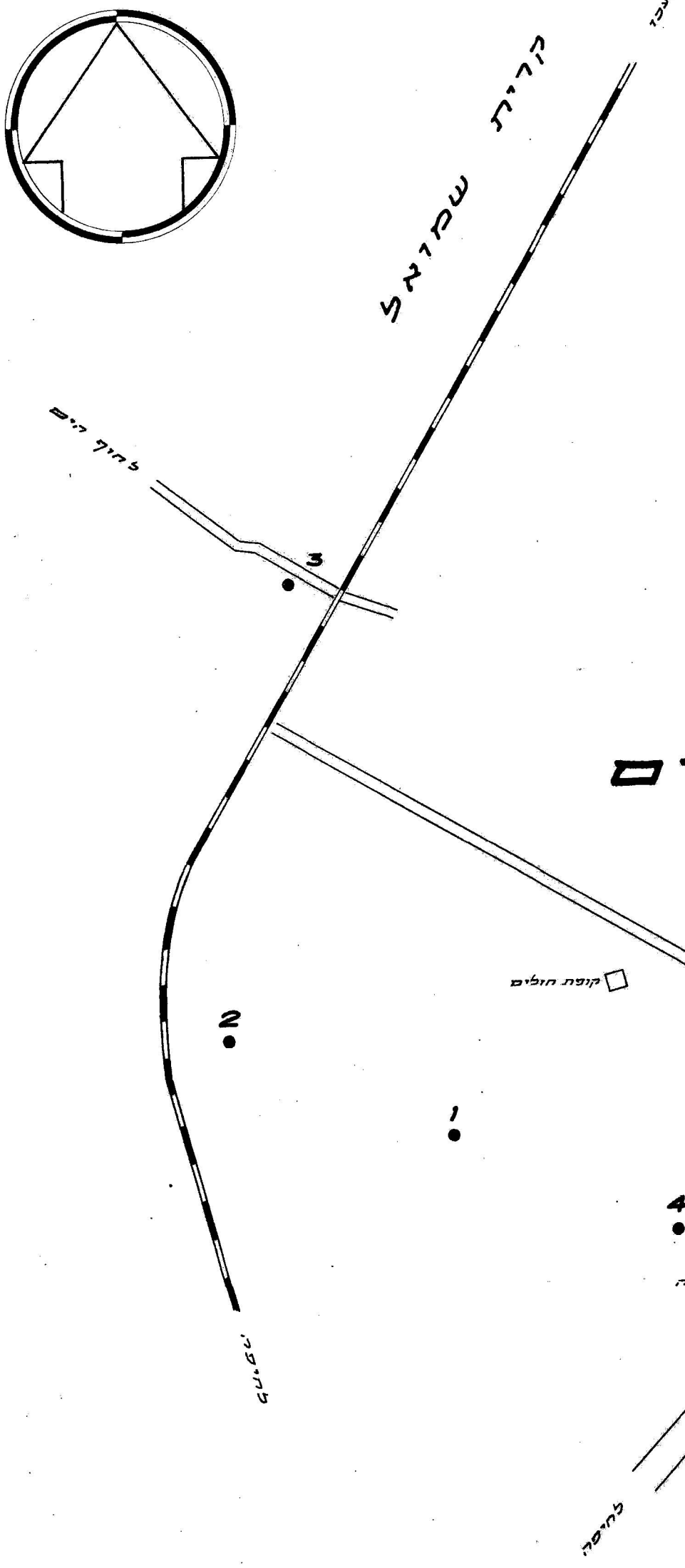
צבי מידב,

עמוס לבנון

מיקום מדידות התנגדות חשמלית

קרית חיים

קנה-מידה 1:10 000

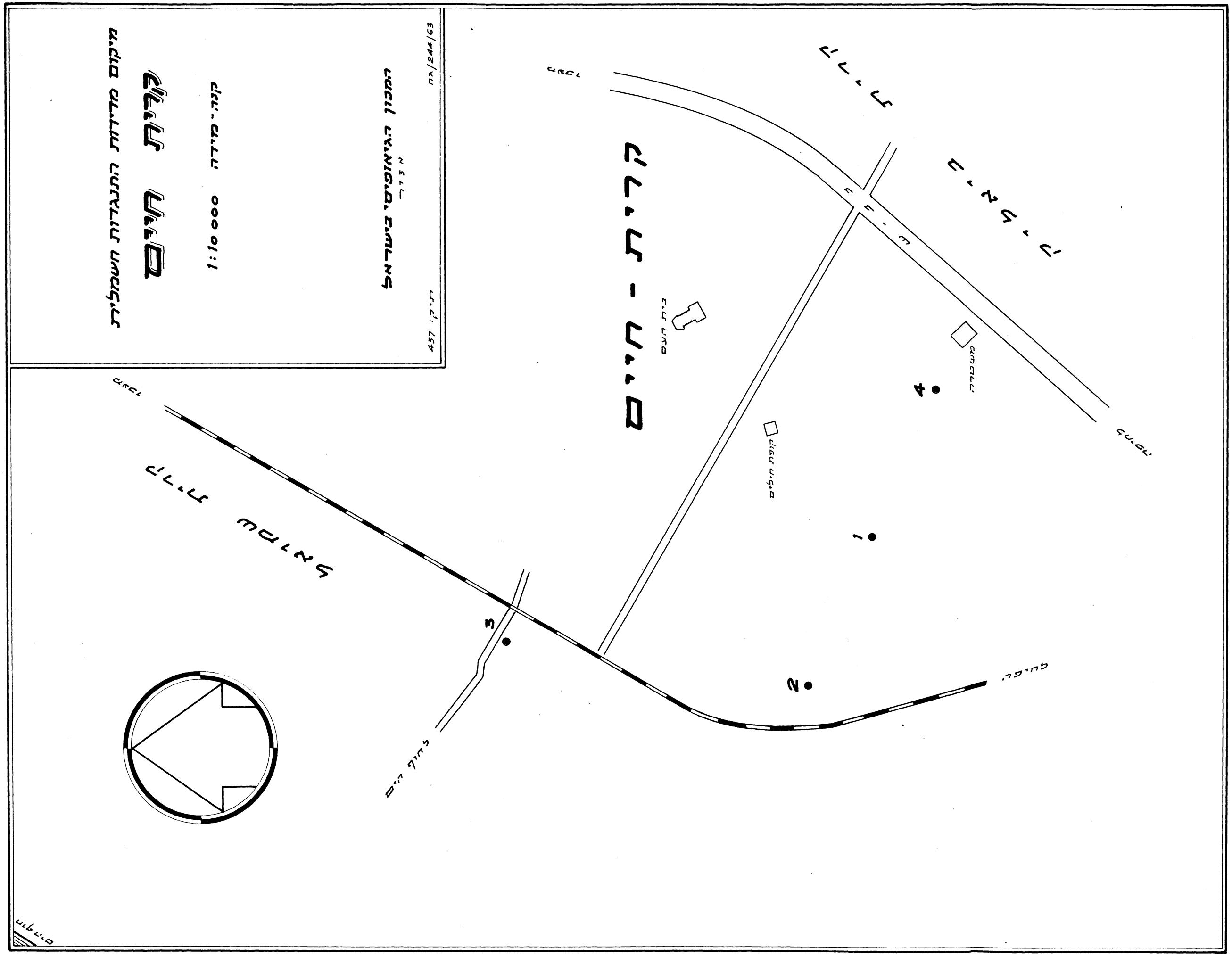


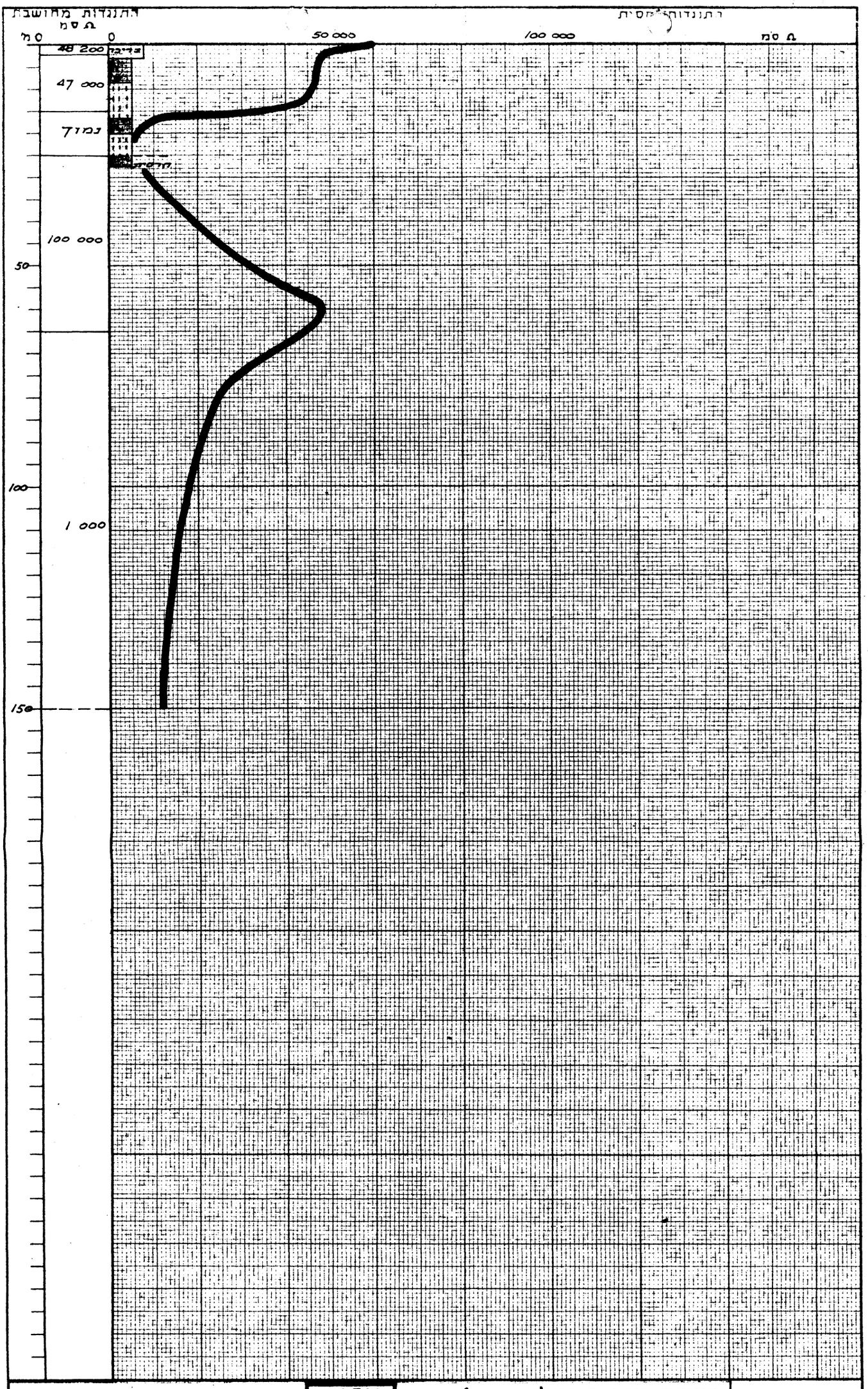
המכון הגיאופיסי בישראל

מ ד ר

גח/244/63

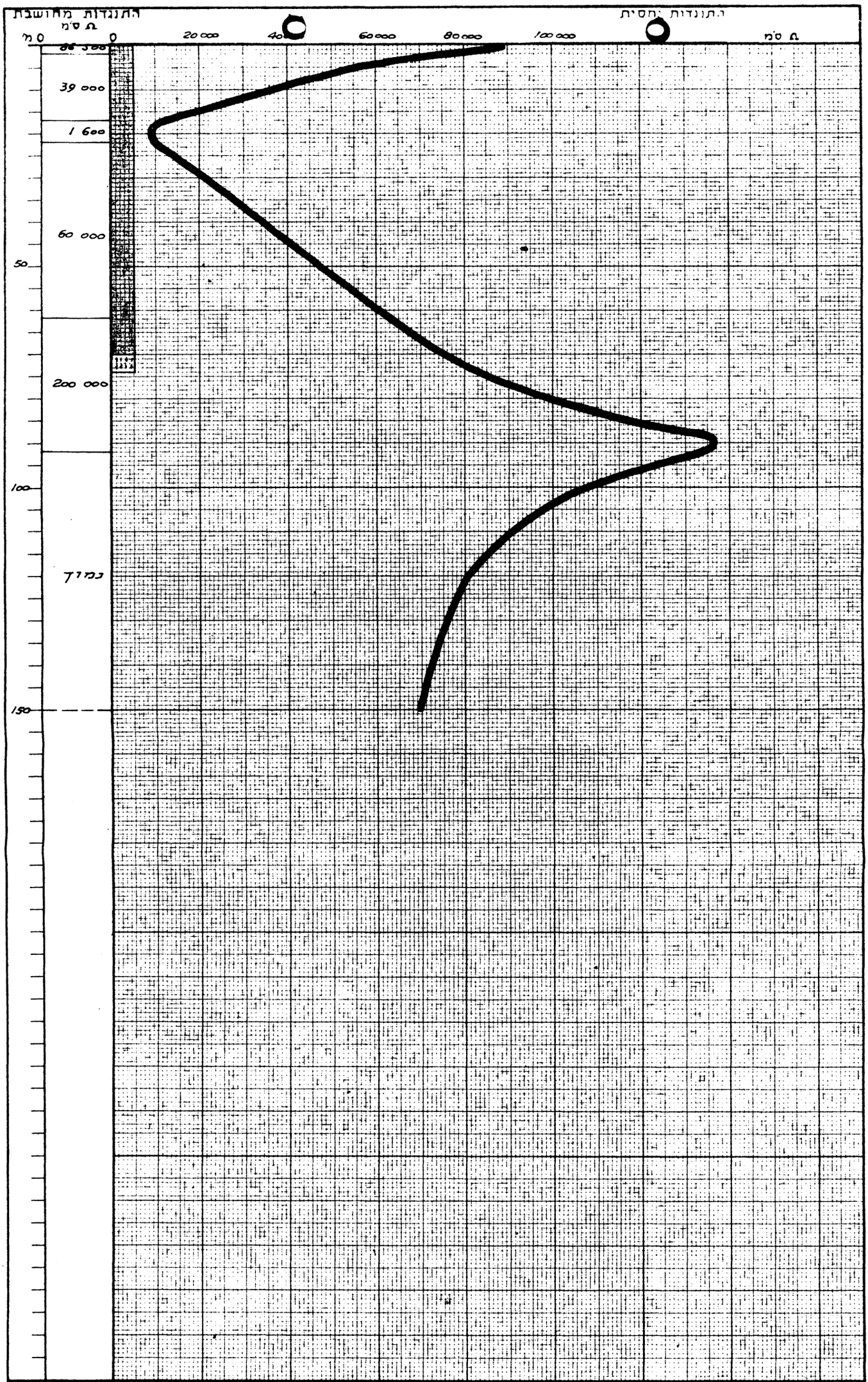
תרשים: 457


כביש 1
כביש 4
כביש 6
כביש 90
כביש 65
כביש 66
כביש 67
כביש 68
כביש 69
כביש 70
כביש 71
כביש 72
כביש 73
כביש 74
כביש 75
כביש 76
כביש 77
כביש 78
כביש 79
כביש 80
כביש 81
כביש 82
כביש 83
כביש 84
כביש



קרית חיים	457	מדידה גיאו-חשמלית מס. 1	
ע"י באר מ'	נובה: // מ' מ	נ.צ.: 24705 - 15665	63/244/בת
SCHLUMBERGER			

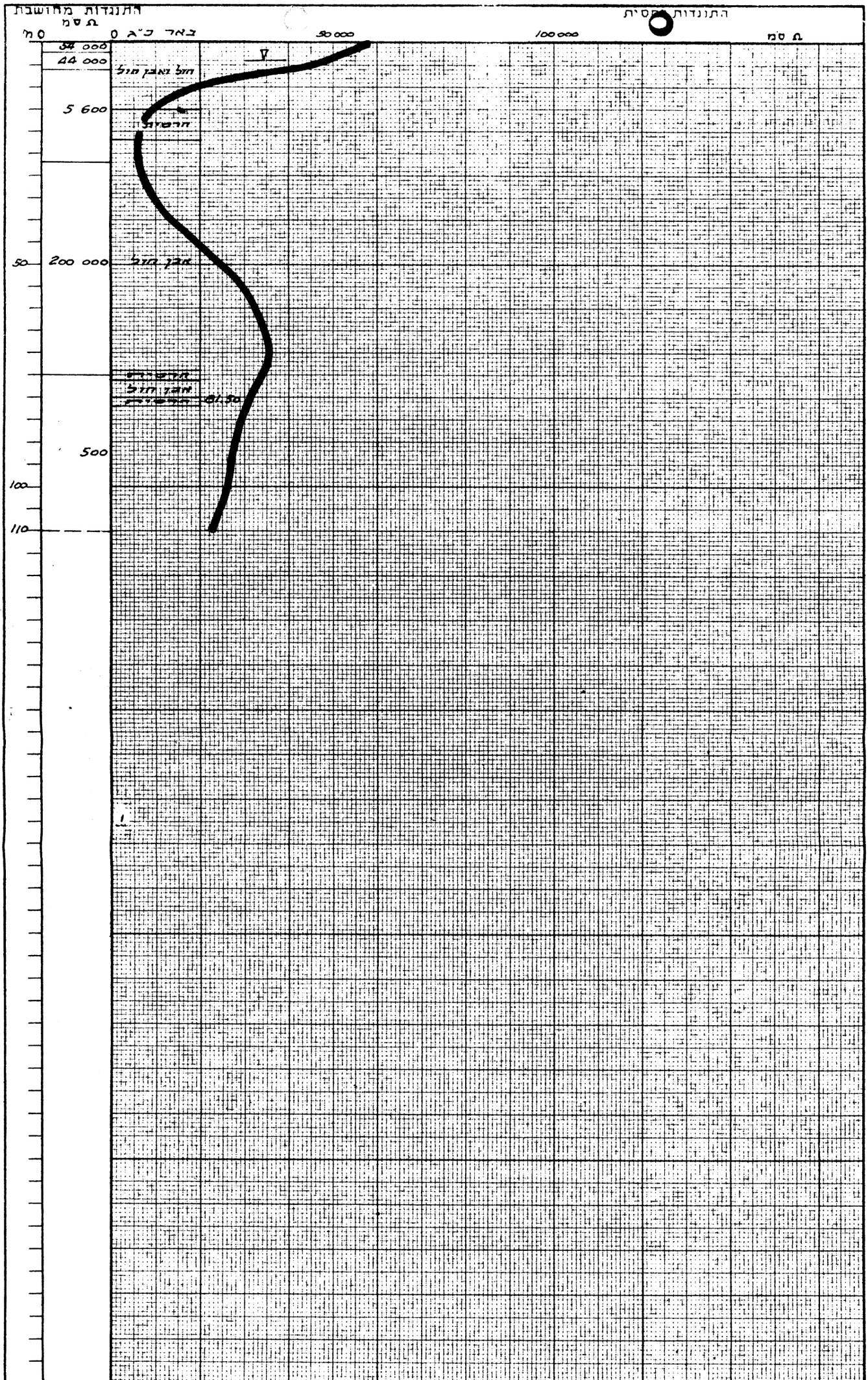
המכון הגיאופיסי בישראל



קריית חיים	457	מדידה גיאו-חשמלית מס. 2
ע"י זאר כ"ב	גובה: 5 מ'מ	נ.צ.: 15619 - 24710
SCHLUMBERGER		

המכון הגיאופיסי בישראל

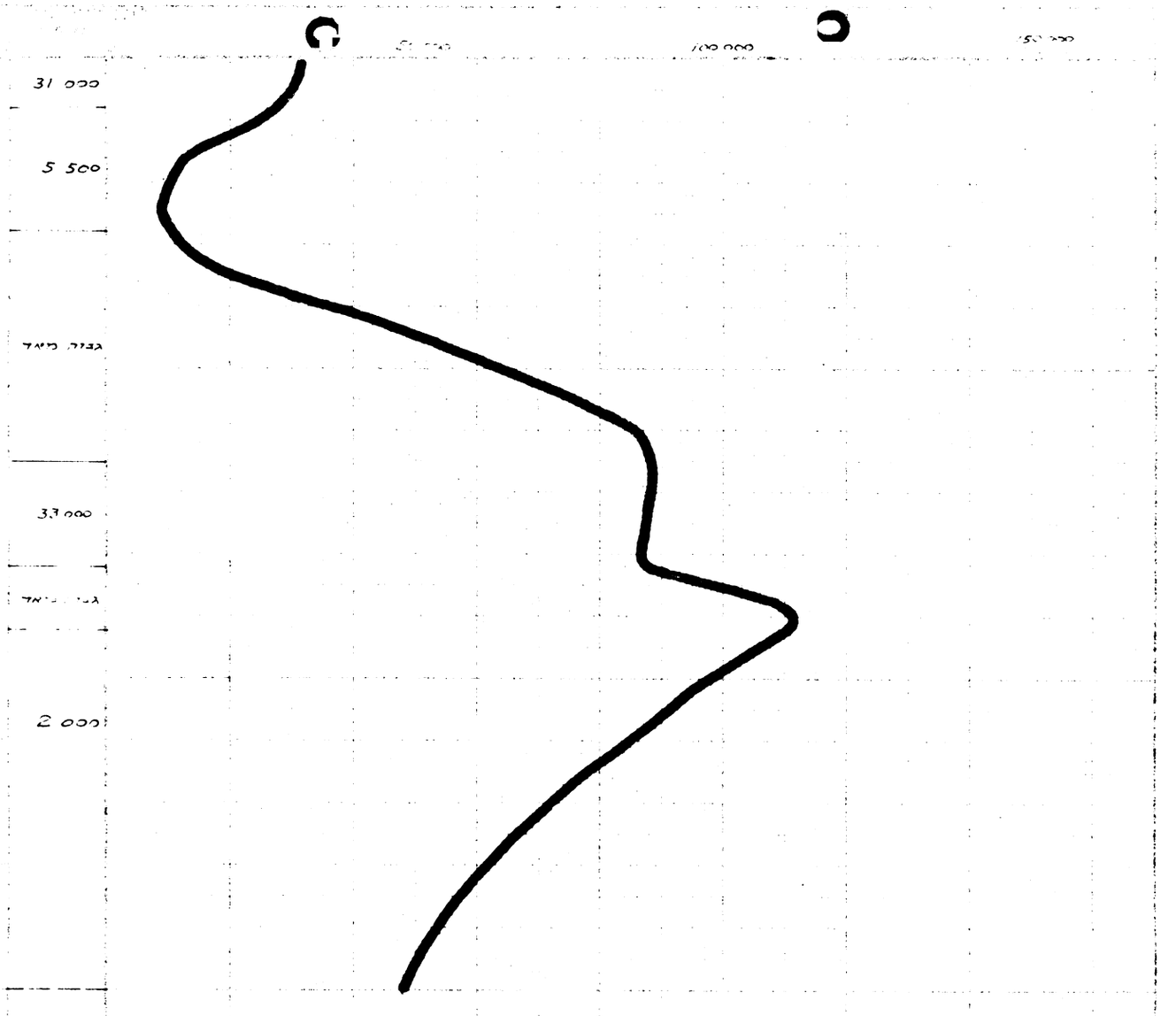
גח/244/63



קדית חיים	457	מדידה גיאו-חשמלית מס. 3
שיד באר כ"ג	גובה: 6.66 מ'	נ.צ.: 156 20 – 248 20
SCHLUMBERGER		

המכון הגיאופיסי בישראל

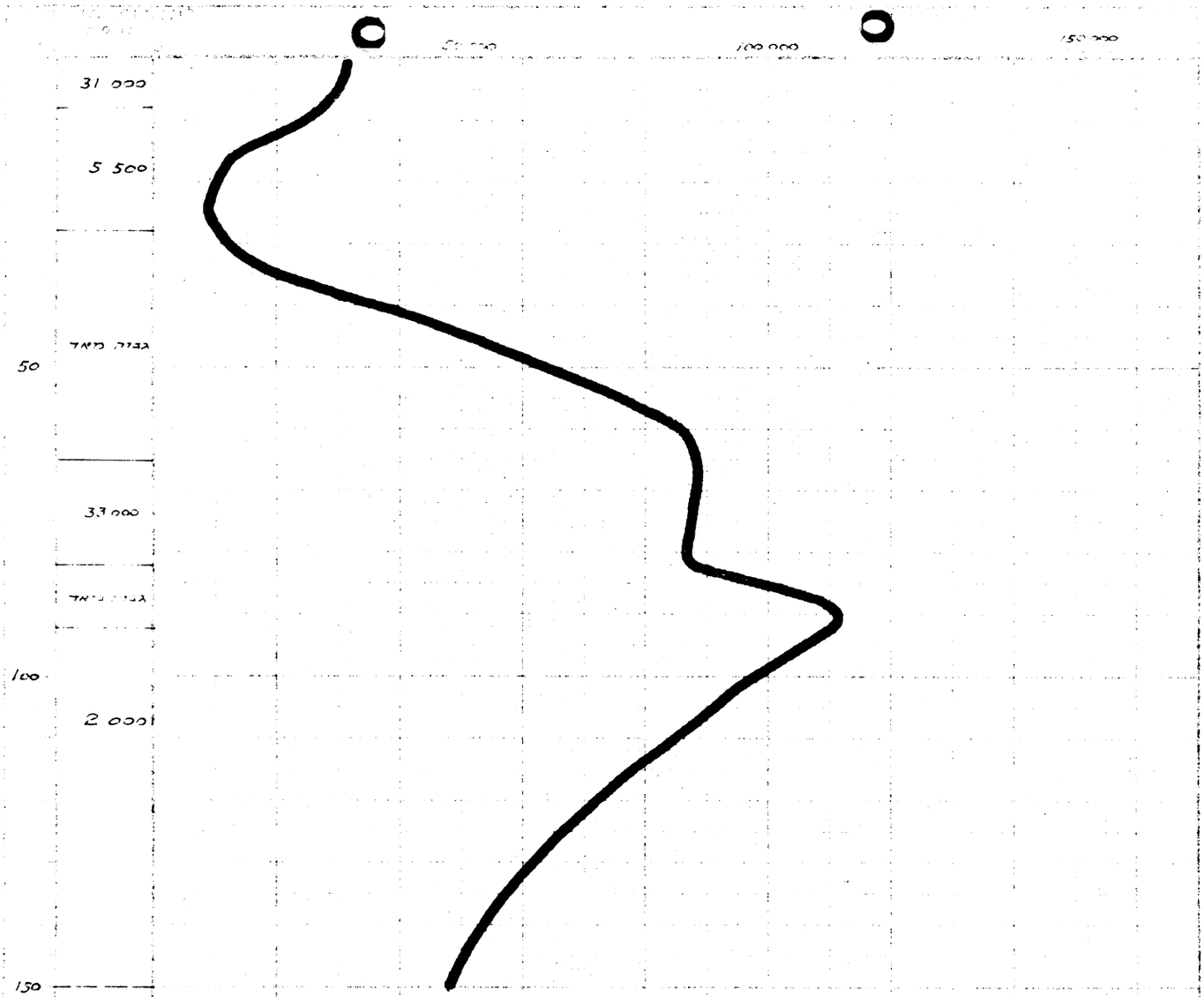
גת/244/63



קרית חיים	457	מדידה ניאו-השוכלית מס 4	
ע"י הנכבדה	10 מ' א	גובה	X 157 04 - 246 90
SCHLUMBERGER		מס' מערכת מגנין המשטרה	

המכון הגיאופיסי בישראל

63/244 גת



קדית חיים	457	מדידה גיאו-חשמלית מס 4		
ע"י הכבידה	10 מ' מ	גובה	157 04 - 246 80	צ
SCHLUMBERGER	100 מ' מערכת מתנין המשטרה			

המכון הגיאופיסי בישראל

63 / 244 / גמ

